Análisis del mercado de alquileres en el Área Metropolitana de Buenos Aires

Estudio descriptivo y segmentación estratégica basada en datos propios

Resumen

El objetivo del presente informe es analizar el mercado de alquileres residenciales en el Área Metropolitana de Buenos Aires (AMBA) a partir de un dataset propio construido mediante técnicas de web scraping aplicadas sobre portales inmobiliarios. El objetivo fue comprender la estructura del mercado, analizar la formación de precios y detectar zonas estratégicas en función de su liquidez y nivel de valuación.

El análisis realizado revela una fuerte concentración de la oferta en CABA, con un claro predominio de departamentos como tipo de propiedad dominante y una segmentación monetaria relevante entre pesos y dólares. A nivel estratégico, el mercado muestra una estructura polarizada: pocas zonas concentran simultáneamente alto valor y alta liquidez, mientras que otras presentan dinamismo con precios relativos inferiores, configurando potenciales áreas de apreciación.

1. Construcción y preparación del dataset

El análisis presentado en este informe se basa en un dataset construido íntegramente mediante técnicas de web scraping aplicadas sobre portales inmobiliarios que publican ofertas activas de alquiler en el Área Metropolitana de Buenos Aires.

La extracción de datos no partió de una base estructurada preexistente, sino que requirió diseñar un proceso programático capaz de adaptarse a estructuras HTML heterogéneas y dinámicas. Cada portal presenta diferencias en su arquitectura interna, nomenclatura de campos y mecanismos de paginación. En algunos casos, fue necesario implementar estrategias adicionales para manejar cambios en el layout y eventuales restricciones técnicas.

Una vez obtenidos los registros individuales, se consolidaron en un archivo CSV para cada portal para posteriormente ser unificados en una base consolidada.

El dataset final quedó compuesto por **41591 publicaciones activas**, distribuidas en **184 localidades** y agrupadas en **4 regiones principales (CABA, GBA Norte, GBA Sur y GBA Oeste)**. Durante el proceso de depuración se eliminaron **1790 registros duplicados o inconsistentes**, lo que permitió garantizar mayor robustez en el análisis posterior.

La variable precio representó uno de los principales desafíos técnicos. El mercado inmobiliario argentino opera simultáneamente en pesos y dólares, por lo que fue necesario

convertir todos los valores a una moneda común para permitir comparaciones consistentes. La conversión se realizó utilizando un tipo de cambio fijo correspondiente al momento del estudio, permitiendo así construir la variable precio por metro cuadrado en términos homogéneos.

Asimismo, se aplicaron filtros estructurales para detectar y eliminar outliers extremos tanto en superficie como en precio. Este proceso permitió preservar la representatividad de las medidas centrales, particularmente la mediana, que fue adoptada como estadística principal debido a su robustez frente a distribuciones asimétricas.

El resultado fue una base consolidada, estandarizada y validada, apta para análisis descriptivo y segmentación estratégica.

Todo el proceso de extracción, limpieza, normalización y análisis fue desarrollado programáticamente en Python utilizando librerías como Pandas y Matplotlib, lo que garantiza trazabilidad, consistencia metodológica y reproducibilidad completa del pipeline de datos. La automatización del flujo de trabajo permite replicar el estudio ante nuevas capturas de información y extender el análisis sin depender de procesos manuales.

1.1 Limitaciones del Estudio

Como todo análisis basado en datos observados, el presente estudio presenta limitaciones que deben ser explicitadas.

En primer lugar, el dataset refleja oferta publicada y no contratos efectivamente cerrados. Por lo tanto, los precios analizados representan valores de publicación y no necesariamente valores de cierre.

En segundo lugar, la conversión de dólares a pesos se realizó utilizando el tipo de cambio oficial correspondiente al día 27 de Febrero del 2026, resultando en una conversión de ARS 1430 = 1 USD. En un contexto macroeconómico volátil, estas variaciones en el tipo de cambio pueden alterar las comparaciones en el tiempo.

Asimismo, el estudio no incorpora dimensión temporal ni series históricas. Se trata de un corte transversal del mercado, lo que impide analizar tendencias dinámicas o evolución de precios.

Finalmente, la clasificación regional se realizó mediante reglas programáticas basadas en denominaciones de zona, lo que podría implicar pequeñas imprecisiones en casos fronterizos o nomenclaturas ambiguas.

Estas limitaciones no invalidan los resultados, pero sí delimitan el alcance interpretativo del estudio.

2. Estructura del mercado

El análisis comienza con una caracterización estructural del mercado de alquileres en el AMBA. Antes de analizar precios o liquidez, resulta fundamental comprender cómo se distribuye la oferta en términos territoriales y tipológicos.

La distribución geográfica de publicaciones evidencia una concentración significativa en la Ciudad Autónoma de Buenos Aires, seguida por GBA Norte, mientras que GBA Sur y GBA Oeste presentan una menor participación relativa.

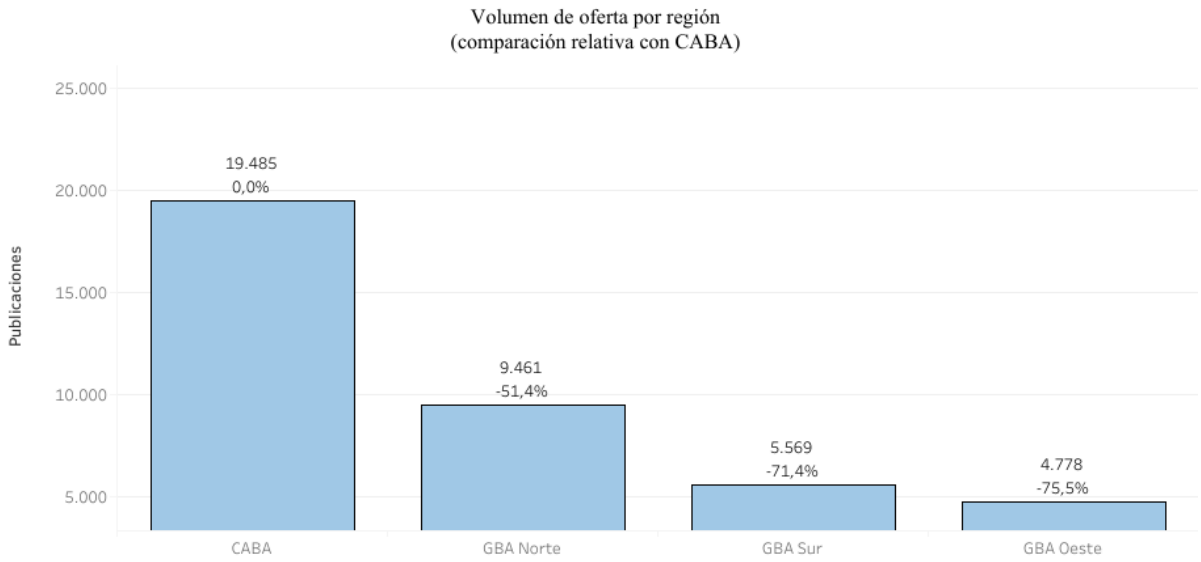

La diferencia no es marginal. CABA concentra aproximadamente el doble de publicaciones que GBA Norte y más de tres veces el volumen de GBA Sur o GBA Oeste. Esto sugiere que la capital funciona como núcleo estructural del mercado, tanto en términos de densidad urbana como de dinamismo inmobiliario.

La distribución por tipo de propiedad refuerza esta lectura.

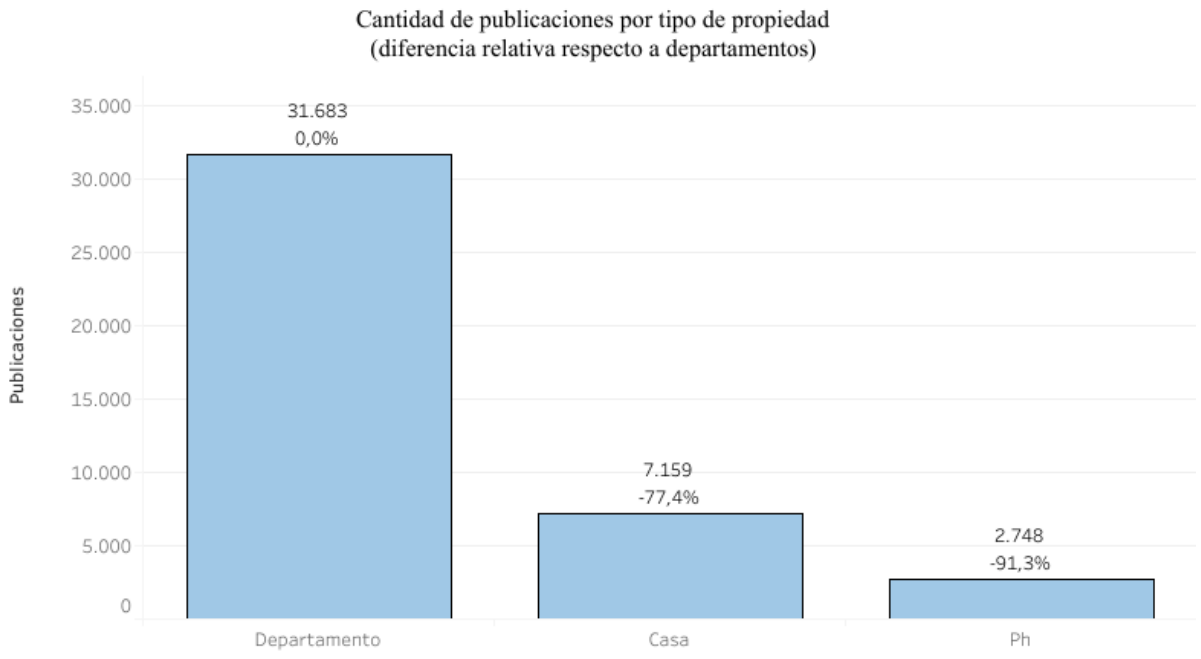

El predominio del departamento es claro. El mercado de alquiler en el AMBA está estructurado principalmente alrededor de unidades verticales, lo que es consistente con la configuración urbana de CABA y los corredores consolidados del conurbano norte.

Sin embargo, no todas las regiones presentan la misma composición interna. La siguiente visualización permite observar cómo varía la participación de casas, departamentos y PH según región.

Distribución porcentual de propiedades por región

Region	Casa	Departamento	Ph
CABA	2,1%	93,9%	3,9%
GBA Norte	42,8%	51,0%	6,3%
GBA Oeste	18,6%	68,8%	12,6%
GBA Sur	23,3%	65,6%	11,1%
Grand Total	16,9%	76,5%	6,6%

En CABA, la participación del departamento es abrumadoramente dominante, mientras que en GBA Norte aumenta significativamente la proporción de casas. Esto refleja diferencias estructurales en el patrón urbano y en la configuración socioeconómica de cada región.

Este primer bloque permite concluir que el mercado presenta una fuerte concentración geográfica y tipológica, con CABA como epicentro y el departamento como activo predominante.

3. Formación de precios y segmentación territorial

Una vez comprendida la estructura de la oferta, el siguiente paso consiste en analizar la formación de precios.

El precio por metro cuadrado constituye el indicador central del estudio, ya que permite comparar propiedades de distinta superficie bajo una misma métrica.

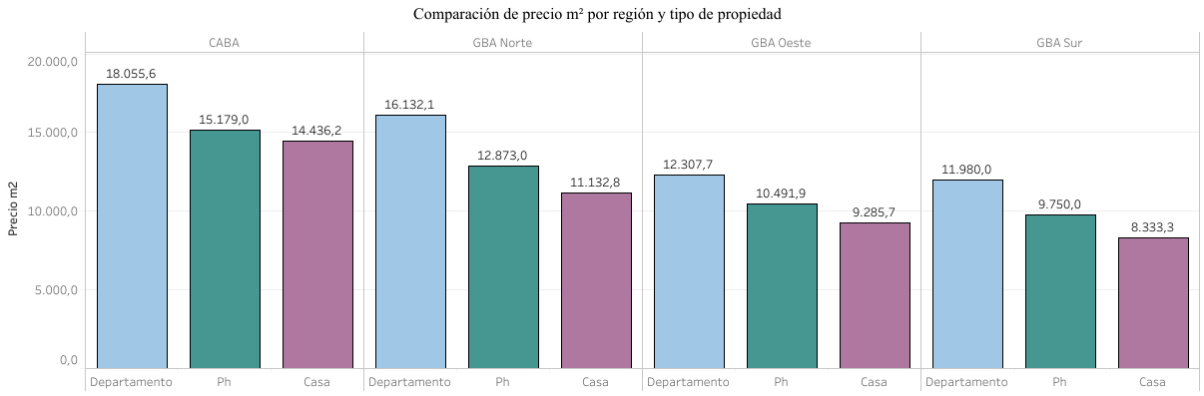

La diferencia regional es clara. CABA presenta los valores más elevados de precio por metro cuadrado en todas las tipologías, con especial concentración en departamentos. GBA Norte se posiciona en segundo lugar, mientras que GBA Sur y GBA Oeste muestran niveles sensiblemente inferiores.

Esta estratificación no solo es regional sino también tipológica. El departamento tiende a presentar mayor precio por m² que casas y PH, especialmente en zonas de alta densidad.

La comparación por moneda permite observar otra dimensión estructural del mercado.

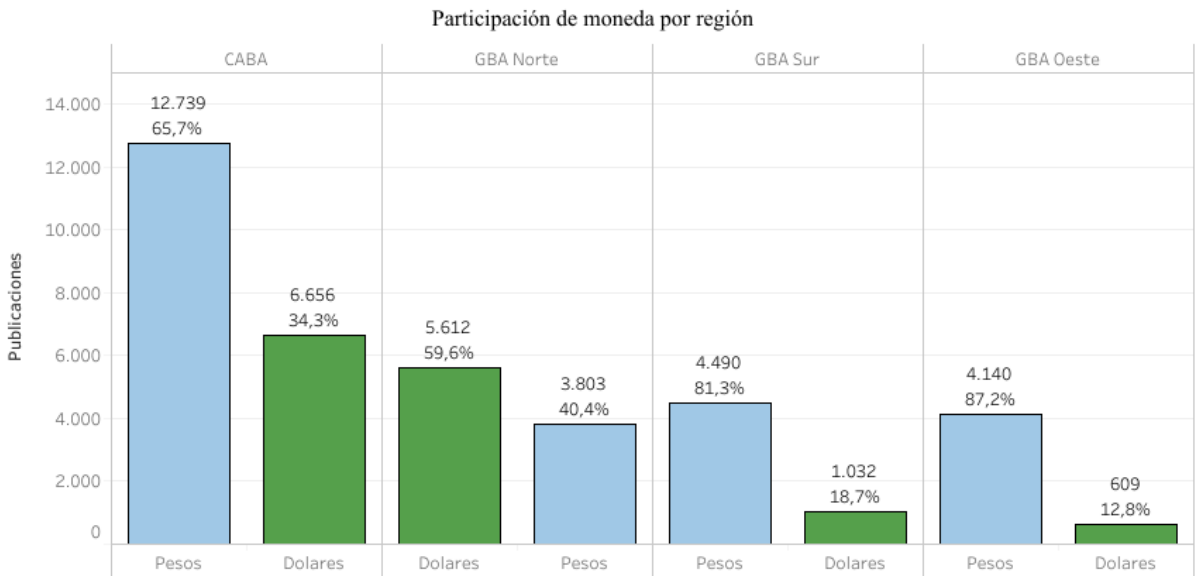

En CABA y GBA Norte se observa mayor presencia relativa de publicaciones en dólares, mientras que en GBA Sur y Oeste predomina el peso argentino. Esta segmentación monetaria introduce una capa adicional de diferenciación socioeconómica dentro del mercado.

Finalmente, para comprender la dispersión territorial del valor, se presenta el ranking de zonas con mayor precio por metro cuadrado.

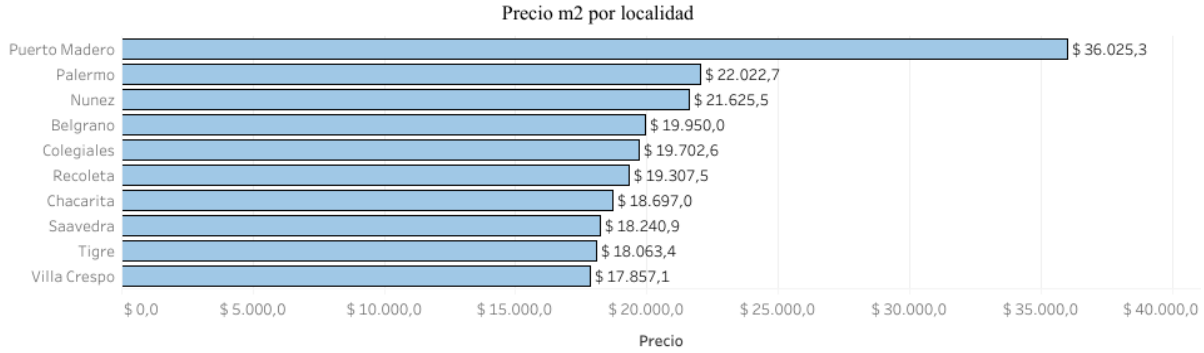

Aquí se evidencia la existencia de nodos altamente concentrados de valor, con Puerto Madero como caso extremo. Estos polos premium no solo elevan la mediana regional, sino que funcionan como referencias de mercado dentro del sistema urbano.

Este bloque confirma que el mercado no es homogéneo: presenta gradientes claros de valor y segmentación tanto territorial como monetaria.

3.1 El peso de las expensas en el costo de alquiler

El análisis del mercado de alquileres suele concentrarse principalmente en el valor del alquiler publicado. Sin embargo, en gran parte del mercado urbano el costo real de habitar una propiedad no está determinado únicamente por el alquiler mensual, sino también por las expensas asociadas al mantenimiento del edificio. Estas incluyen gastos comunes vinculados a servicios, administración, mantenimiento de infraestructura y, en muchos casos, seguridad o amenities.

Por este motivo, incorporar las expensas al análisis permite obtener una visión más completa del **costo efectivo de vivienda**, así como comprender mejor las diferencias estructurales entre distintos segmentos del mercado.

Relación entre expensas y alquiler

El primer indicador analizado fue el **ratio entre expensas y alquiler**, que permite estimar qué proporción del costo mensual total corresponde a gastos de mantenimiento del edificio.

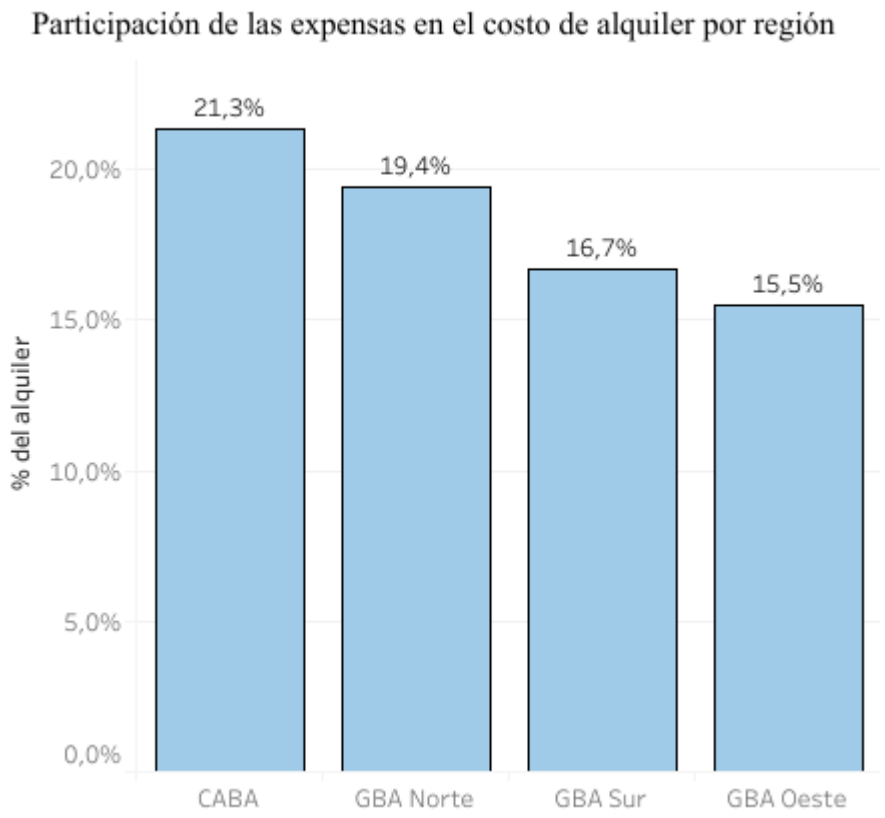

Los resultados muestran que las expensas representan una fracción relevante del costo de vivienda. En términos agregados, la mediana del ratio expensas/alquiler se ubica aproximadamente en torno al **15–20 % del valor del alquiler**. Esto implica que, en promedio, el costo total de habitar una propiedad supera el precio publicado del alquiler en aproximadamente una quinta parte.

En términos prácticos, esto significa que un alquiler publicado de 800.000 ARS suele implicar un costo real cercano a 920.000 -- 960.000 ARS una vez incorporadas las expensas. Este fenómeno es particularmente importante desde el punto de vista de la accesibilidad habitacional, ya que el precio publicado del alquiler puede subestimar de forma significativa el gasto mensual efectivo del hogar.

Diferencias regionales

El peso relativo de las expensas no es homogéneo entre regiones. Al segmentar el análisis por región del AMBA se observa que las expensas tienden a representar una proporción mayor del alquiler en **CABA** que en el conurbano.

Esto responde principalmente a diferencias en la estructura urbana. En la ciudad predominan edificios en altura con mayor complejidad de mantenimiento, presencia frecuente de portería, infraestructura común más extensa y, en muchos casos, amenities como gimnasios, piscinas o espacios de uso común. Estas características incrementan los costos de mantenimiento del consorcio y, por lo tanto, las expensas mensuales.

En contraste, en gran parte del conurbano la oferta inmobiliaria presenta una mayor proporción de viviendas de baja densidad, edificios más pequeños o propiedades horizontales, lo que reduce el peso relativo de las expensas dentro del costo total de vivienda.

Como resultado, el costo efectivo de vivir en CABA tiende a ser mayor no solo por el nivel del alquiler sino también por el peso adicional de los costos comunes.

Diferencias por tipo de propiedad

Las diferencias también se observan claramente cuando se analiza el mercado según **tipo de propiedad**.

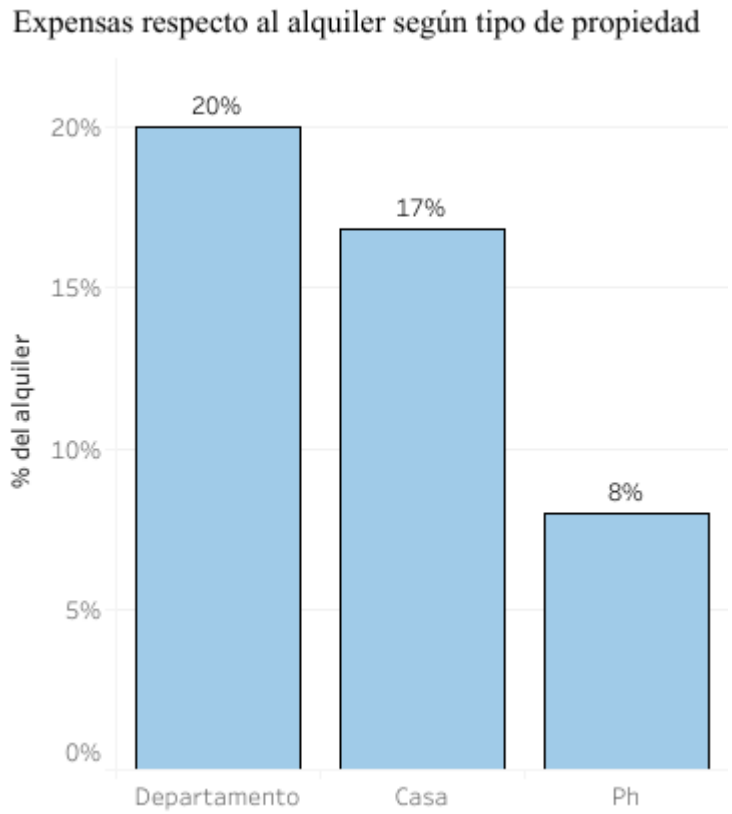

Los departamentos concentran prácticamente la totalidad de los casos con expensas significativas, mientras que las casas y los PH presentan costos de mantenimiento considerablemente menores o directamente inexistentes. Esto se debe a que en las viviendas horizontales los gastos de mantenimiento suelen recaer directamente sobre el propietario o se distribuyen entre muy pocas unidades.

En consecuencia, el ratio expensas/alquiler funciona también como un indicador indirecto del **tipo de estructura edilicia predominante en cada zona**. Zonas con mayor presencia de edificios en altura tienden a mostrar niveles más elevados de expensas, mientras que áreas con mayor proporción de viviendas horizontales presentan costos comunes más reducidos.

El costo total de vivienda

Incorporar las expensas permite construir una medida más completa del costo de habitar una propiedad:

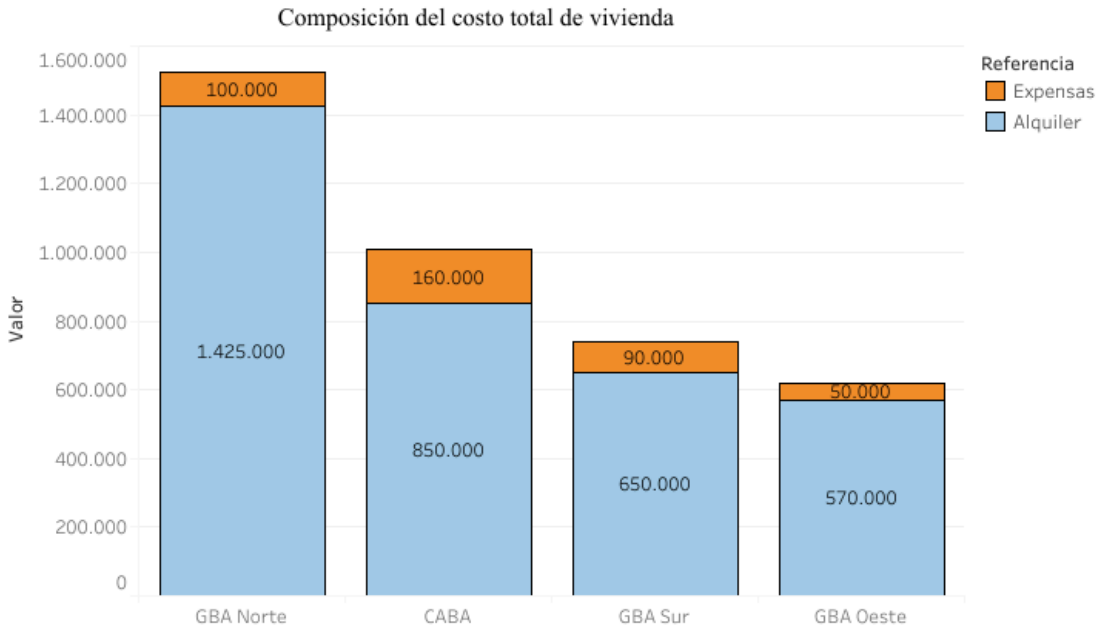

Este enfoque revela que dos propiedades con alquileres similares pueden presentar costos reales significativamente distintos cuando se consideran los gastos comunes del edificio. En algunos casos, propiedades con alquileres relativamente bajos pueden terminar teniendo un costo total comparable a unidades más caras debido a expensas elevadas.

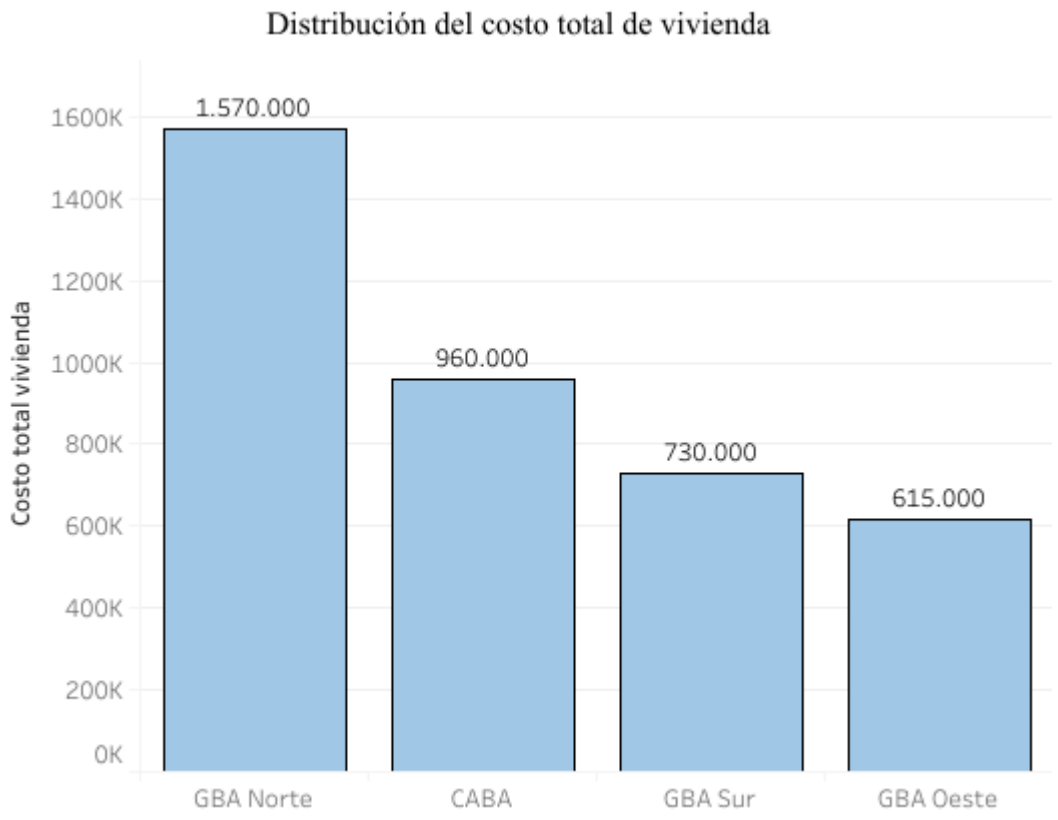

Desde el punto de vista del análisis de mercado, esto introduce una dimensión adicional en la evaluación de accesibilidad y competitividad entre zonas. El precio del alquiler publicado no siempre refleja el costo efectivo que enfrenta el inquilino, lo que puede influir en la percepción de valor relativo entre distintas ubicaciones.

Implicancias estructurales del mercado

El análisis de expensas también permite observar ciertos patrones estructurales del mercado inmobiliario urbano.

En primer lugar, las expensas tienden a ser mayores en zonas donde predominan edificios más nuevos o con mayor cantidad de servicios comunes. Esto sugiere que las expensas funcionan, en cierta medida, como un **indicador indirecto de calidad edilicia o complejidad de infraestructura del edificio**.

En segundo lugar, la dispersión observada en el ratio expensas/alquiler indica la coexistencia de distintos submercados dentro del mismo sistema urbano. Algunos edificios presentan estructuras de costos relativamente moderadas, mientras que otros, especialmente aquellos con amenities o servicios adicionales, muestran niveles de expensas considerablemente más elevados.

Estos patrones reflejan la heterogeneidad del parque inmobiliario del AMBA y evidencian que el costo de mantenimiento del edificio constituye un componente relevante en la estructura del mercado de alquileres.

Expensas por metro cuadrado y tamaño de la propiedad

Un último aspecto interesante surge al analizar la relación entre **expensas por metro cuadrado y superficie de la propiedad**.

En muchos edificios una parte importante de los costos del consorcio corresponde a gastos fijos que se distribuyen entre las unidades, independientemente de su tamaño. Como resultado, las unidades más pequeñas suelen enfrentar expensas relativamente más altas en términos de costo por metro cuadrado.

Esto implica que departamentos de menor superficie pueden presentar ratios de expensas/m² más elevados que unidades de mayor tamaño dentro del mismo edificio. Este fenómeno introduce una dinámica adicional en el análisis de accesibilidad, ya que los departamentos pequeños —que suelen ser elegidos por hogares con menor capacidad de pago— pueden enfrentar una carga proporcionalmente mayor de gastos comunes.

En conjunto, el análisis de expensas permite ampliar la comprensión del mercado de alquileres más allá del precio publicado, incorporando una dimensión clave del costo efectivo de vivienda. Esta perspectiva resulta particularmente útil para evaluar accesibilidad, estructura edilicia y diferencias territoriales dentro del sistema urbano del AMBA.

4. Dinámica de liquidez y concentración

El análisis de precios, considerado de manera aislada, ofrece una visión parcial del mercado. Si bien la mediana de precio por metro cuadrado permite identificar niveles relativos de valorización, no explica por sí sola la profundidad ni la estabilidad estructural de cada zona. Para evaluar con mayor precisión la solidez del mercado es necesario incorporar una segunda dimensión: el volumen de publicaciones, utilizado aquí como un proxy de liquidez y nivel de actividad.

La combinación de precio relativo y volumen permite construir una lectura más integral. No se trata únicamente de identificar dónde los valores son más elevados, sino de comprender qué tan activos y consolidados son esos mercados. En términos analíticos, el cruce entre ambas variables permite aproximarse al grado de madurez de cada micro-mercado dentro del ecosistema inmobiliario del AMBA.

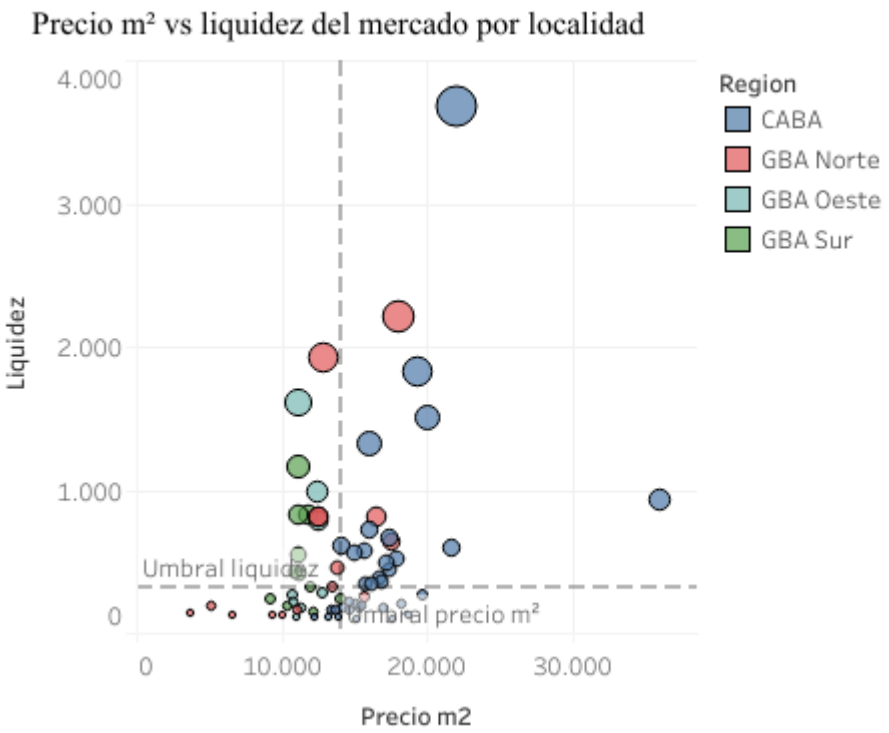

El gráfico de dispersión posiciona cada zona en un plano bidimensional definido por dos ejes: en el eje vertical se representa el volumen de publicaciones, mientras que en el eje horizontal se ubica la mediana de precio por metro cuadrado en pesos. Las líneas punteadas incorporadas en el gráfico corresponden a las medianas globales de ambas variables y actúan como umbrales analíticos que dividen el espacio en cuatro cuadrantes estructurales.

Esta división permite observar comportamientos diferenciados. En el cuadrante superior derecho se concentran aquellas zonas que combinan precios elevados con alto nivel de actividad. Se trata de mercados consolidados, donde la valorización relativa se sostiene en el tiempo y la liquidez es consistente. La coexistencia de ambas variables sugiere una demanda estructural fuerte y un posicionamiento estable dentro del mercado.

En contraste, el cuadrante superior izquierdo agrupa zonas con precios altos pero bajo volumen. Estos casos suelen corresponder a nichos específicos o segmentos premium menos líquidos, donde el valor relativo es elevado pero la rotación es menor. La escasa actividad puede estar asociada a una oferta limitada o a características muy particulares del mercado local.

El cuadrante inferior derecho presenta una configuración especialmente interesante desde el punto de vista analítico: zonas con volumen significativo pero con precios por debajo de la mediana global. Este patrón revela mercados activos cuya valorización relativa aún no converge hacia los niveles superiores. Desde una perspectiva dinámica, estas áreas pueden interpretarse como espacios con potencial de apreciación o como segmentos donde la demanda es sostenida pero el precio todavía no refleja plenamente esa intensidad.

Finalmente, el cuadrante inferior izquierdo concentra zonas de menor actividad y menor valor relativo. En estos casos, la combinación de baja liquidez y menor precio sugiere mercados secundarios o periféricos, con menor centralidad dentro del sistema.

Un aspecto relevante del gráfico es que la distribución de puntos no es uniforme ni lineal. Se observan agrupamientos en determinados rangos de precio y volumen, lo que evidencia la existencia de micro-mercados con dinámicas propias. Esta clusterización sugiere que el mercado de alquileres no responde a una lógica homogénea, sino que está segmentado por estructuras territoriales diferenciadas.

La incorporación del volumen como variable analítica transforma la lectura tradicional basada exclusivamente en precios. El mercado aparece entonces no solo estratificado por valor, sino también por intensidad de actividad y grado de madurez relativa.

A partir de los umbrales definidos por las medianas globales, se identifican como zonas Premium aquellas que se ubican simultáneamente por encima del precio mediano por metro cuadrado y del volumen mediano de publicaciones. Este criterio permite aislar mercados que combinan valorización y liquidez, dos condiciones que, en conjunto, suelen asociarse con estabilidad estructural.

El ranking de estas zonas permite observar cuáles concentran mayor actividad dentro del segmento de alto valor. No se trata únicamente de identificar las áreas más caras, sino aquellas que, además de sostener precios elevados, mantienen un flujo constante de oferta. En términos económicos, estos mercados actúan como nodos centrales del sistema: atraen capital, concentran visibilidad y presentan una rotación sostenida.

Desde una perspectiva analítica, las zonas Premium funcionan como referencias estructurales del mercado. Su comportamiento permite establecer comparaciones y detectar desvíos en otros segmentos, constituyéndose en puntos de anclaje dentro de la estructura territorial del alquiler.

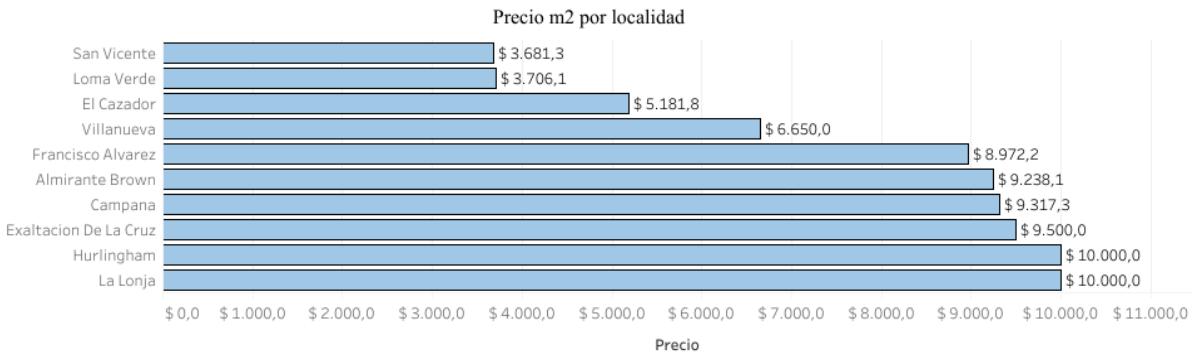

En paralelo, se identifican como zonas con Potencial aquellas que presentan un volumen de publicaciones superior a la mediana global pero un precio por metro cuadrado inferior a dicho umbral. Esta configuración es particularmente significativa porque revela mercados activos cuya valoración relativa aún se mantiene por debajo del promedio estructural.

La existencia de actividad sostenida indica que estas zonas no son marginales ni de baja demanda. Por el contrario, el flujo de publicaciones sugiere dinamismo y presencia de oferta

constante. La menor valoración relativa puede interpretarse como un margen de convergencia futura o como un estadio intermedio dentro del proceso de maduración del mercado.

A diferencia de los mercados Premium, donde el precio y la liquidez ya se encuentran alineados en niveles altos, las zonas con Potencial exhiben una tensión estructural entre actividad y valor. Desde una mirada estratégica, este desfase puede constituir un espacio de oportunidad, especialmente si factores externos como, infraestructura, conectividad, transformación urbana, entre otros, impulsan procesos de valorización progresiva.

5. Implicancias estratégicas y lectura estructural del mercado

El análisis conjunto de valorización relativa y liquidez territorial permite avanzar desde una descripción cuantitativa hacia una interpretación estructural del mercado de alquileres en el AMBA. La segmentación entre zonas consolidadas, nichos premium, áreas dinámicas con potencial y mercados secundarios no constituye simplemente una clasificación descriptiva, sino una radiografía del grado de madurez y profundidad de cada micro-mercado.

El mercado no presenta una estructura homogénea. Por el contrario, exhibe una fuerte concentración de actividad en determinados nodos territoriales que actúan como polos de atracción. Estas zonas combinan precios elevados con alto volumen de publicaciones, lo que sugiere estabilidad en la demanda y capacidad de absorción constante de oferta. Desde una perspectiva económica, estos espacios funcionan como mercados relativamente eficientes: el precio refleja información consolidada y la liquidez reduce fricciones entre oferta y demanda.

Sin embargo, el hallazgo más relevante no se encuentra necesariamente en estos mercados consolidados, sino en las zonas clasificadas como Potencial. En ellas se observa una actividad significativa acompañada de niveles de precio por metro cuadrado inferiores a la mediana global. Este desfase entre intensidad de actividad y valorización relativa puede interpretarse como una señal de transición estructural dentro del sistema territorial del mercado inmobiliario.

Existen varias hipótesis posibles para explicar este fenómeno. Puede tratarse de zonas con mejoras recientes en conectividad, infraestructura o servicios urbanos cuyo impacto aún no se refleja completamente en los precios de mercado. También puede responder a cambios en las preferencias habitacionales, como desplazamientos desde zonas tradicionales hacia áreas que ofrecen una mejor relación entre precio, superficie y accesibilidad. En cualquier caso, la coexistencia de volumen sostenido y menor valoración relativa introduce la posibilidad de convergencia futura entre estos territorios y los nodos consolidados del mercado.

Desde una lógica de análisis de mercado, estas áreas representan espacios donde el riesgo relativo podría estar compensado por un mayor margen de apreciación potencial. No constituyen mercados especulativos de baja actividad, sino territorios con dinámica real de

oferta cuya valorización todavía no alcanza niveles comparables con los polos consolidados. En este sentido, funcionan como corredores de transición dentro de la estructura territorial del mercado.

A esta lectura basada en precio y liquidez se suma una dimensión adicional analizada en el presente estudio: el costo efectivo de vivienda. La incorporación de las expensas permite observar que el precio publicado del alquiler no siempre refleja de manera completa el gasto mensual que enfrentan los hogares. En determinados segmentos del mercado, especialmente en edificios con mayor complejidad de mantenimiento o presencia de servicios comunes, las expensas pueden representar una fracción significativa del costo total de habitar una propiedad.

Esta dimensión introduce una capa adicional de heterogeneidad dentro del sistema. Zonas con niveles de alquiler similares pueden presentar diferencias relevantes en el costo efectivo de vivienda una vez incorporados los gastos comunes asociados al mantenimiento edilicio. En consecuencia, la estructura territorial del mercado no sólo se organiza en función del nivel de precios y del volumen de actividad, sino también del peso relativo de los costos de mantenimiento que caracterizan a cada tipo de desarrollo inmobiliario.

El contraste entre zonas Premium y zonas Potencial revela, en definitiva, que la estructura del mercado no responde exclusivamente a una jerarquía de precios. La liquidez cumple un rol determinante en la configuración territorial del sistema. Allí donde precio y volumen convergen en niveles altos, el mercado se comporta como un núcleo estable y maduro. Allí donde el volumen es alto pero el precio no acompaña, se abre un espacio de tensión estructural que puede derivar en procesos de ajuste, convergencia o revalorización futura.

Esta lectura integrada permite posicionar el análisis más allá de una simple comparación de valores nominales. El mercado de alquileres del AMBA aparece como un sistema dinámico, compuesto por polos consolidados, corredores de transición y periferias de menor densidad económica. Comprender estas diferencias resulta fundamental para interpretar correctamente los indicadores y evitar conclusiones simplistas basadas únicamente en niveles de precio.

En síntesis, la segmentación construida a partir del cruce entre valorización relativa, actividad del mercado y costo efectivo de vivienda ofrece una herramienta robusta para distinguir estabilidad, madurez y potencial de crecimiento dentro del sistema inmobiliario urbano. Este enfoque no solo describe la situación actual del mercado, sino que también sugiere trayectorias posibles en función de la estructura territorial observada.

6. Consideraciones técnicas, limitaciones y proyección analítica

El presente análisis se construye sobre una base de datos obtenida mediante técnicas de web scraping aplicadas a portales inmobiliarios del AMBA. Este proceso implicó diversos desafíos técnicos vinculados a la extracción estructurada de información no estandarizada,

la normalización semántica de variables territoriales y la consolidación de múltiples fuentes en un dataset unificado y coherente.

La primera etapa del trabajo consistió en la captura automatizada de datos, enfrentando variaciones en la estructura HTML de los portales, inconsistencias en las nomenclaturas geográficas y diferencias en la forma de expresar variables como moneda, superficie o expensas. La necesidad de depurar valores atípicos extremos, homogeneizar denominaciones territoriales y segmentar correctamente los precios según moneda fue central para garantizar la calidad analítica posterior.

Uno de los principales desafíos fue la coexistencia de alquileres expresados tanto en pesos como en dólares dentro de las publicaciones. La conversión a una moneda común permitió realizar análisis agregados comparables, pero también exigió mantener segmentaciones paralelas para evitar distorsiones estructurales en determinados segmentos del mercado. Del mismo modo, el tratamiento de outliers en precios y superficies fue realizado bajo criterios conservadores, priorizando la consistencia estadística sin eliminar observaciones válidas que representan segmentos premium reales del mercado.

Adicionalmente, el análisis incorporó el tratamiento específico de la variable expensas, cuya estructura presenta particularidades propias dentro de los portales inmobiliarios. Las expensas suelen expresarse mediante distintos formatos, unidades monetarias o incluso pueden estar ausentes en determinadas publicaciones. Por este motivo fue necesario desarrollar un proceso de extracción y normalización específico para esta variable, transformando valores textuales en una variable numérica homogénea que permitiera su análisis cuantitativo.

A partir de esta normalización se construyeron indicadores derivados que ampliaron significativamente el alcance del estudio. Entre ellos se incluyen el ratio entre expensas y alquiler, el cálculo del costo total de vivienda y la estimación de expensas por metro cuadrado. Estos indicadores permitieron extender el análisis más allá del precio publicado del alquiler e incorporar una dimensión clave vinculada al costo efectivo de habitar una propiedad.

En términos metodológicos, es importante señalar que el volumen de publicaciones se utilizó como proxy de liquidez del mercado. Esta aproximación permite capturar la intensidad de actividad dentro de cada zona, pero no sustituye información directa sobre tiempos de absorción, rotación efectiva o transacciones concretadas. El dataset refleja oferta publicada, no operaciones cerradas, lo que introduce una limitación inherente al análisis.

Asimismo, la clasificación territorial en regiones (CABA, GBA Norte, GBA Oeste y GBA Sur) responde a criterios administrativos y funcionales. Si bien esta segmentación facilita la lectura estructural del mercado, el funcionamiento del mercado inmobiliario suele responder a dinámicas microterritoriales más complejas que pueden atravesar estos límites formales.

Desde una perspectiva estadística, el estudio es predominantemente descriptivo. Se utilizaron medidas robustas como la mediana para mitigar el impacto de distribuciones asimétricas y valores extremos, especialmente en variables como precio por metro

cuadrado y costo total de vivienda. No obstante, el análisis no incorpora aún modelización predictiva ni técnicas de inferencia causal, lo cual constituye una línea de desarrollo futura.

En términos de proyección analítica, el presente estudio constituye una base sólida para desarrollos metodológicos de mayor complejidad. Una línea natural de evolución consiste en la estimación de modelos econométricos que permitan identificar los determinantes del precio por metro cuadrado, incorporando variables explicativas como tipología de propiedad, superficie, región y características estructurales de cada zona. Este enfoque permitiría avanzar desde la descripción hacia la cuantificación del impacto marginal de cada atributo en la formación de precios.

Asimismo, la incorporación de dimensión temporal ampliará significativamente el alcance del análisis. La construcción de series históricas permitiría evaluar la volatilidad, detectar cambios de régimen y estimar tendencias estructurales del mercado, particularmente relevantes en un contexto macroeconómico dinámico como el argentino. Un análisis longitudinal abriría la puerta a estudiar ciclos inmobiliarios, convergencias territoriales y procesos de revalorización urbana.

Otra extensión posible radica en la aplicación de técnicas de aprendizaje no supervisado, como algoritmos de clustering, para identificar tipologías territoriales emergentes sin imponer segmentaciones predefinidas. Este enfoque permitiría descubrir agrupamientos naturales dentro del mercado que podrían no coincidir estrictamente con divisiones administrativas tradicionales, revelando patrones estructurales ocultos.

Finalmente, la integración de variables exógenas —como indicadores socioeconómicos, niveles de infraestructura, conectividad urbana o accesibilidad al transporte— permitiría enriquecer el modelo explicativo y contextualizar la formación de precios dentro de una lógica territorial más amplia. La combinación de información inmobiliaria con datos urbanos ampliará considerablemente la capacidad interpretativa del estudio.

La construcción del dataset final, luego de múltiples etapas de limpieza, unificación y validación, permitió transformar información heterogénea y ruidosa en una base analíticamente consistente. Este proceso constituye, en sí mismo, una parte sustantiva del valor del trabajo: la calidad del análisis depende directamente de la calidad del dato.

En conclusión, el informe presenta una radiografía estructural del mercado de alquileres en el AMBA basada en evidencia cuantitativa, integrando tanto dimensiones de valorización territorial —como precio por metro cuadrado y liquidez— como indicadores vinculados al costo efectivo de vivienda, incorporando el impacto de las expensas dentro de la estructura del mercado. Si bien el enfoque adoptado es descriptivo, la metodología aplicada sienta bases sólidas para desarrollos analíticos más avanzados y para la construcción futura de modelos predictivos.

El mercado analizado no aparece como un sistema uniforme, sino como una red de micro-mercados con distintos grados de madurez, liquidez y valoración relativa. Comprender esta heterogeneidad resulta clave para cualquier aproximación rigurosa al estudio del fenómeno inmobiliario urbano.